BD Forêt® version 2

Généralités

L'Institut national de l'information géographique et forestière (IGN) propose une nouvelle édition (version 2) de la carte des types de formation végétale. Ses principales caractéristiques sont les suivantes :

- une couche parfaitement superposable avec la couche « Végétation multi-thèmes » de la composante topographique du Référentiel à Grande Échelle (BD Topo®/RGE) ;
- une nomenclature nationale ;
- un type de formation végétale attribué à chaque plage cartographiée supérieure ou égale à 50 ares (5 000 m²).

Voici quelques-unes des caractéristiques de la carte forestière du département des Vosges (BD Forêt® version 2) et quelques chiffres qui en sont déduits.

Nomenclature

La nomenclature nationale utilisée pour cette édition de la carte forestière prend en compte la couverture du sol, la densité du couvert, la composition du peuplement et les essences qu'il est possible de distinguer par photo-interprétation. Hiérarchique selon quatre niveaux, le niveau le plus fin est renseigné pour les entités supérieures à deux hectares.

Réalisation

Cette production cartographique s'appuie sur la BD Ortho®. L'information est interprétée sur cet orthophotoplan avec l'appui de diverses informations (anciennes cartes, etc.). De nombreuses tournées sur le terrain sont également réalisées pour lever les incertitudes identifiées lors du travail de bureau.

Année de référence (photographies aériennes BD Ortho®)	2010
Année de diffusion	2014
Surface du département	589 950 ha
Surface cartographiée	315 373 ha
Taux de boisement	53,0 %

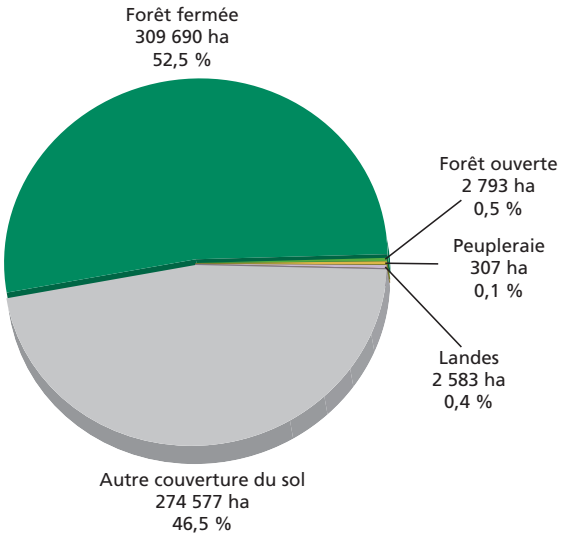

Chantraine

Orthophotoplan
en Infrarouge Couleur
(BD Ortho®)

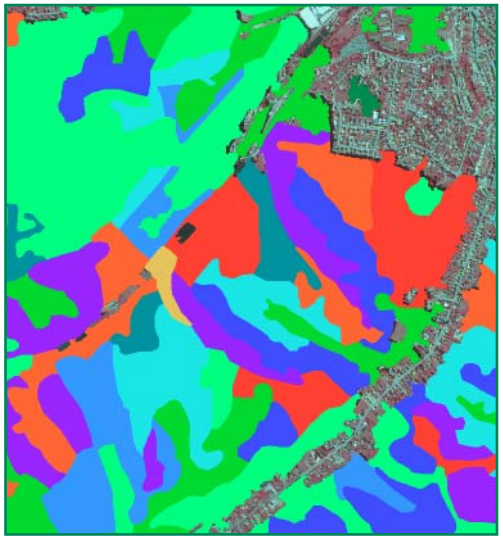

Type de formation végétale

IGN
Institut national de l'information géographique et forestière

BD Forêt® version 2

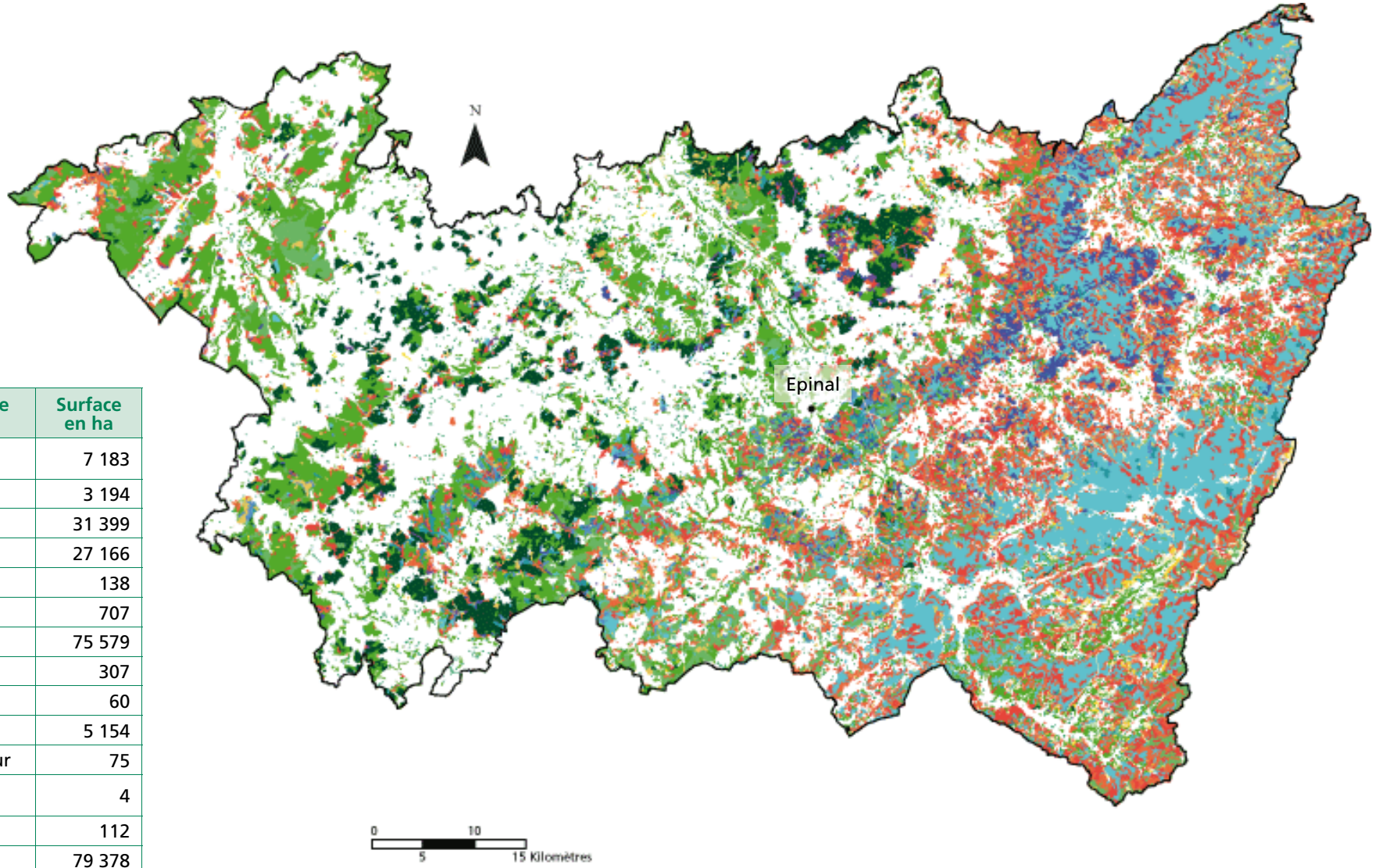

Type de formation végétale	Surface en ha
Jeune peuplement ou coupe rase ou incident	7 183
Feuillus purs en îlots	3 194
Chênes décidus purs	31 399
Hêtre pur	27 166
Robinier pur	138
Autre feuillu pur	707
Mélange de feuillus	75 579
Peupleraie	307
Conifères purs en îlots	60
Pin sylvestre pur	5 154
Pin laricio ou pin noir pur	75
Pin à crochets ou pin cembro pur	4
Mélange de pins purs	112
Sapin ou épicéa	79 378
Mélèze pur	236
Douglas pur	3 135
Autre conifère pur autre que pin, sapin, épicéa, douglas ou mélèze	34
Mélange d'autres conifères	3 582
Mélange de conifères	8 427
Mélange de feuillus prépondérants et conifères	38 331
Mélange de conifères prépondérants et feuillus	25 798

Type de formation végétale	Surface en ha
Forêt ouverte avec coupe rase ou incident	1
Forêt ouverte de feuillus purs	1 261
Forêt ouverte de conifères purs	454
Forêt ouverte à mélange de feuillus et conifères	1 078
Lande ligneuse	1 506
Formation herbacée	1 077

IGN
INSTITUT NATIONAL DE L'INFORMATION GÉOGRAPHIQUE ET FORESTIÈRE